2024.4

道路附属物における点検結果登録時の作業内容

目次

1　作業概要
1.1　名寄せ
1.2　クレンジング
1.3　維持的作業一覧表
1.4　施設種別毎の作業概要

2　小規模附属物
2.1　維持的作業一覧表の登録
2.2　道路施設基本データの登録

3　門型標識等
3.1　名寄せ
3.2　クレンジング
3.3　道路施設基本データの登録

4　横断歩道橋
4.1　クレンジング

履歴

Ver	変更内容	改訂
v01	初版	2022.12
v02	2.4と3.3「道路施設基本データの登録」に、データの補完・補正について追記	2023.3
v03	操作マニュアル添付用に修正	2023.4
V04	名寄せ・クレンジング作業を変更	2024.4

注釈

各様式の作成の仕方等は道路管理者に異なるため、詳細の作業内容については、道路管理者とご相談の上、実施して下さい。

1.　作業概要

1.1.　名寄せ

同一の施設の各データ（77 条調査データ、点検記録様式 or 横断歩道橋カルテ、道路施設基本データ）を紐づける作業。

【名寄せのイメージ】

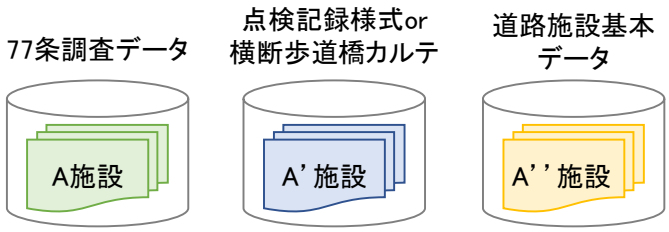

AとA’とA’’は、同じ施設であることを確認し、
データ同士を紐づける

1.2.　クレンジング

同一の施設の各データ（77 条調査データ、点検記録様式 or 横断歩道橋カルテ、道路施設基本データ）で、共通項目にも関わらず記載が異なっている場合に、記載を統一する作業。

【クレンジングの例】

77 条調査データ		横断歩道橋カルテ		道路施設基本データ	
横断歩道橋名	Ａ横断歩道橋	名称	Ａ’横断歩道橋	名称	Ａ’’横断歩道橋
橋長	１００ｍ	橋長	１００．５ｍ	橋長	１０１．０ｍ

77 条調査データ		横断歩道橋カルテ		道路施設基本データ	
横断歩道橋名	Ａ横断歩道橋	名称	Ａ横断歩道橋	名称	Ａ横断歩道橋
橋長	１００．５ｍ	橋長	１００．５ｍ	橋長	１００．５ｍ

1.3.　維持的作業一覧表

標識板の交換や照明灯の灯具交換（LED 化）、安定器交換等、仕様変更に該当せず、道路施設基本データが作成されない作業についての記録。

【維持的作業一覧表の事例】

整理番号1	事務所名	出張所名	路線	距離標	補修年月	内容（工事名）	原因
0000000	●●	●●	●号	○k○	202203	灯具交換（●●工事）	LED化
0000000	△△	△△	△号	○k○	202201	自動点滅器交換（●●工事）	故障のため

施設を特定できる項目　　道路施設台帳に登録する項目

1.4. 施設種別毎の作業概要

令和５年度までと作業内容が変更されています。

横断歩道橋	門型標識等	小規模附属物
・クレンジングを実施（変更無し）。	・道路施設基本データと 77 条調査データの名寄せは別途実施する予定のため、名寄せ済の「道路施設基本データ・77 条調査データ」と「点検記録様式」の名寄せを実施。 ・クレンジングを実施（変更無し）。	・名寄せ・クレンジングは不要。 （名寄せ・クレンジングは別途実施）

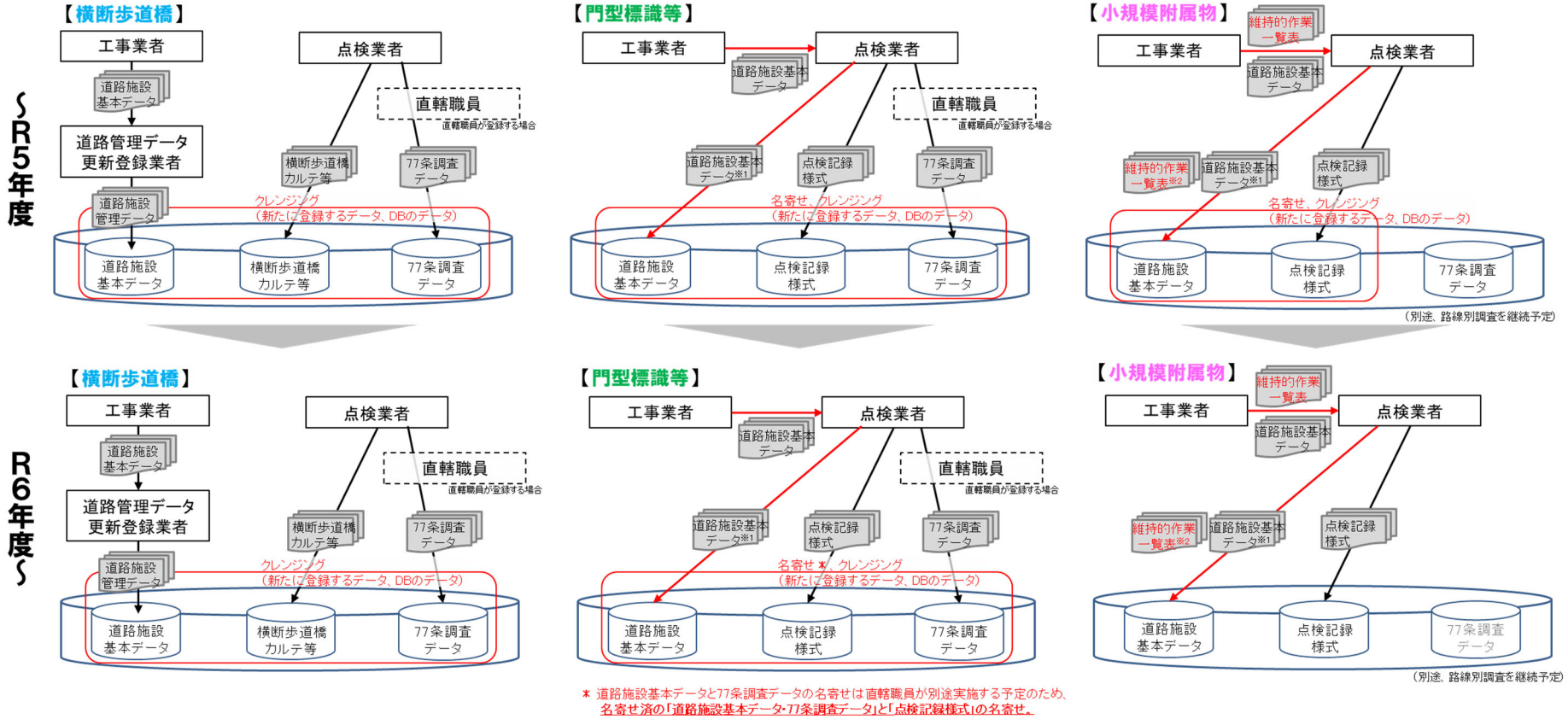

＊ 道路施設基本データと77条調査データの名寄せは直轄職員が別途実施する予定のため、名寄せ済の「道路施設基本データ･77条調査データ」と「点検記録様式」の名寄せ。

※1 設計変更の対象とする。
道路施設基本データについて、道路管理データ更新登録業務での登録も可能とするが、その場合は、横断歩道橋カルテ等や77条調査データと登録内容に不整合が無いか確認を行ったうえで登録を行うものとする。
※2 標識板の交換や照明灯の灯具交換(LED化)、安定器交換等、仕様変更に該当せず、道路施設基本データが作成されない工事の場合

2.　小規模附属物（門型標識以外の標識、照明）

小規模附属物で実施する作業の概要は、以下の通りです。

	名寄せ	クレンジング	維持的作業一覧表※2の登録	道路施設基本データの登録※1
準備段階			• 点検した施設の維持的作業一覧表を、発注者から受け取る	• 点検した施設の新たに登録する道路施設基本データを、発注者から受け取る
点検結果DB登録時			• 維持的作業一覧表を、ＤＢの道路施設基本データの【補修歴】に登録	• 道路施設基本データをＤＢに登録※1

※1　設計変更の対象とする。
　　道路施設基本データについて、道路管理データ更新登録業務での登録も可能とするが、その場合は、点検記録様式と記載内容を統一して登録を行うものとする。

※2　標識板の交換や照明灯の灯具交換(LED化)、安定器交換等、仕様変更に該当せず、道路施設基本データが作成されない工事の場合

2.1. 維持的作業一覧表の登録

① 発注者から「維持的作業一覧表」を受け取ってください。

② 受け取った「維持的作業一覧表」の内容を、附属物ＤＢの道路施設基本データの「補修歴」に入力してください。

【維持的作業一覧表(一例)】

整理番号1	事務所名	出張所名	路線	距離標	補修年月	内容(工事名)	原因
0000000	●●	●●	●号	○k○	202203	灯具交換(●●工事)	LED化
0000000	△△	△△	△号	○k○	202201	自動点滅器交換(●●工事)	故障のため

施設を特定できる項目　　道路施設台帳に登録する項目

【道路施設台帳】

●●開発局　　●●開発建設部　　●●道路事務所

名称 : #	路線名 : 国道○号　現旧区分 : 現道	整理番号1 : ●●
所在地 :	距離標 : ○.○　△	調整年月日 : #
		改訂年月日 : #

【補修歴】

整理番号2	補修年月	内　容	備　考(原因等)

【補修歴】に登録

2.2. 道路施設基本データの登録

① 点検する施設が初回点検で新設の道路施設基本データがある場合や、補修工事後で道路施設基本データがある場合は、発注者からデータを受け取り、附属物ＤＢに登録してください。

② 登録するデータは、「2.2 クレンジング」を行い、共通項目について、点検記録様式と記載内容を統一して登録してください。

※ 登録方法については、道路附属物 DB や http://www.rirs.or.jp/tenken-db/touroku.php に掲載されている操作マニュアルを参照。

※ 設計変更の対象となります。

※ 道路管理データ更新登録業務での登録も可能としますが、その場合は、点検記録様式と記載内容を統一して登録して下さい。

※ 道路施設基本データに必要な項目が記載されていない場合のデータ補完や、完成図面等との照合によるデータ修正等を行って登録をお願いします。

3.　門型標識等

門型標識等で実施する作業の概要は、以下の通りです。

※1　設計変更の対象とする。
道路施設基本データについて、道路管理データ更新登録業務での登録も可能とするが、その場合は、点検記録様式や77条調査データと記載内容を統一して登録を行うものとする。

3.1. 名寄せ

① 点検する施設の道路施設基本データを、附属物ＤＢから取得します。

※点検する施設が初回点検で、「3.3 道路施設基本データの登録」と合わせて作業する場合は附属物ＤＢ上にデータがなく、発注者からの貸与となります。その場合、②で示す「施設キー」は、道路施設基本データを附属物ＤＢに登録後にしか表示されませんので、<u>最初に道路施設基本データを登録</u>して下さい。

② 道路施設基本データから取得した道路施設台帳で、「施設キー」を確認します。


道路照明台帳

施設キー ●●●●●●●

（地方整備局名）　（事務所名）　（出張所名）

名称 :	路線名 : 国道5号　現旧区分 : 現道	整理番号1 :	
所在地 :	距離標 : 263.1　29	調整年月日 :	#
		改訂年月日 :	#

【基本諸元】

連続・局部の別 : 局部照明	安定器型式 : 一般高力率形	備考 :	
設置区分 : 道路照明	[自動点滅器]	自管理	
設置箇所 : 上り車線	型式 : 光電式		
完成年月 : ?	電流 : #（A）		
灯具型式 : 道路灯 KSC-4（水銀可）	電圧 : #（V）		
照明ポール型式 : ?	[分電盤]		
新設・移設の別 : 新設照明	分電盤型式 : #		
基礎形式 : ベースプレート型	調光回路有無 : #		
配列方式 : #	主幹開閉方式 : #		
表面塗装処理 : 亜鉛メッキ式	分岐開閉方式 : #		
塗装面積 : #㎡	幹線電気方式		
連続照明区間認識番号	相 : （φ）		
: 無し	線数 : #		
[光源]	電圧 : #（v）		
① 種類 : 高圧ナトリウムランプ	分岐電気方式		
型式 : NHF220	相 : #（φ）		
灯数 : 1灯	線数 :		
② 種類 : *	電圧 : #（v）		
型式 : 無し	[関連施設]		
灯数 : *灯	名称 : #		
③ 種類 : *	整理番号 : #		
型式 : 無し			
灯数 : *灯			
[配線]			
引込方式 : 架空単独			
分岐方式 : 架空			
[電力契約]			
契約種別 : 公衆街路灯　B			
契約番号 :			
引込柱名称 :			
支払営業所名 :			

③ 点検記録様式の入力時、「MICHI 施設キー」に入力します。

【入力イメージ】

※ 77 条調査データや点検記録様式の１施設に対して、道路施設基本データが複数施設存在する場合は、複数の「施設キー」をセミコロン（；）で区切って入力してください。

※ 該当する道路施設基本データがない場合は、「0」を入力してください。この場合、77 条調査データと点検記録様式は、管理番号で紐づけすることになるため、「3.2 クレンジング」で、管理番号は特に注意して同じ記載内容になるようにお願いします。

道路施設基本データと 77 条調査データの名寄せを直轄職員が別途実施する予定です。この名寄せが完了すると、77 条調査データと名寄せされた道路施設基本データの MICHI 施設キーが 77 条調査データに入力されますので、77 条調査データから MICHI 施設キーを確認することも可能になります。（点検記録様式は 77 条調査データと共通項目が多いため、77 条調査データから調べる方が容易な場合が多いと思われます）。

3.2. クレンジング

① 以下の「門型標識等 共通項目一覧表」に示す共通項目について、「3.1. 名寄せ」で取得した道路施設基本データ（「3.3 道路施設基本データの登録」をする場合は、発注者から受け取った新たな道路施設基本データも含む）と、今回登録する 77 条調査データ、点検記録様式で、記載の違いがあるか確認します。

＜門型標識等 共通項目一覧表＞

77 条調査データ			標識、照明点検記録様式	道路施設基本データ	
				標識	情報板
施設名	施設名（案内標識、警戒標識、その他（道路標識）、提供装置、収集装置、その他（情報装置））		種別		
	形式（門型）		支柱形式	支柱形式 C	
				支柱形式	
施設設置場所			設置環境	設置箇所 C	設置箇所 C
				設置箇所	設置箇所
施設設置場所	施設名称			名称	名称
路線	路線名		路線名	路線	路線
	道路種別		道路種別		
管理者	管理者名		管理者（局）	地建 C	地建 C
				地建	地建
	事務所名		管理者（事務所）	事務所 C	事務所 C
				事務所	事務所
	出張所名		管理者（出張所）	出張所 C	出張所 C
				出張所	出張所
設置年度（西暦）				施設完成年度	施設完成年度
設置年月			設置年月　年	完成年月	完成年月
			設置年月　月		
管理番号			管理番号		
幅員（m）			道路幅員（m）		
行政区域	都道府県名		所在地（県）	市区町村 C	
				市区町村	
	市区町村名		所在地（市）	市区町村 C	
				市区町村	
位置	起点	緯度	緯度	経度	経度
		経度	経度	緯度	緯度
距離標（キロポスト）			距離標（km）	百米標	百米標
				距離	距離
上り・下り線			上・下別	上り下り区分 C	上り下り区分 C
				上り下り区分	上り下り区分
			表面処理形式	表面塗装処理 C	
				表面塗装処理	
			基礎形式	基礎形式 C	
				基礎形式	

② 記載が異なる場合は、発注者に記載内容を確認し、登録するデータや附属物ＤＢのデータについて、記載内容を統一して登録します。過去の点検結果を書き換えるのではなく、新たに登録する点検結果や施設諸元について記載を統一してください。

【クレンジングの例】

７７条調査データ		標識、照明点検記録様式		道路施設基本データ	
設置年月	１９９５年２月	設置年月　年	１９９８	完成年月	１９９８年２月
		設置年月　月	２		
距離標（キロポスト）	９２．６７０	距離標（km）	９２．５７０	百米標	９２．５
				距離	７０

７７条調査データ		標識、照明点検記録様式		道路施設基本データ	
設置年月	１９９８年２月	設置年月　年	１９９８	完成年月	１９９８年２月
		設置年月　月	２		
距離標（キロポスト）	９２．５７０	距離標（km）	９２．５７０	百米標	９２．５
				距離	７０

※ 各データの登録方法については、道路附属物 DB や http://www.rirs.or.jp/tenken-db/touroku.php に掲載されている操作マニュアルを参照してください。

※ 今後、各データを統合し、共通項目を一元化する予定であり、その際には、

77 条調査データ　→　点検記録様式・カルテ　→　道路施設基本データ

の順に優先して記載内容を残す予定です。

（例．点検記録様式と道路施設基本データの共通項目で記載が異なっている場合、点検記録様式の記載を残し、道路施設基本データの記載を削除）

※ そのため、記載の優先順位の高いデータの記載を修正すれば、必ずしも全てのデータを修正する必要はありません。

	77条調査データ			横断歩道橋カルテ等		道路施設基本データ等		
8	諸元	施設名	横断歩道橋名	datK000_1	名称	D030横断歩道橋基本	14	名称
9	諸元		ﾌﾘｶﾞﾅ	datK000_1	名称フリガナ			
10	諸元	路線	路線名	datK000_1	路線名称	D030横断歩道橋基本	4	路線
12	諸元	架設年度	架設年度(西暦)	datK000_1	架設竣工年	D030横断歩道橋基本	22	施設完成年度
15	諸元	橋長(m)		datK000_2	橋長	D030横断歩道橋基本	51	橋長
16	諸元	通路幅員(m)		datK001	有効幅員	D030横断歩道橋基本	55	幅員
17	諸元	形式区分				D030横断歩道橋基本	36	昇降形式C
	諸元					D030横断歩道橋基本	37	昇降形式
19	諸元	管理者	管理者名	datJ000	地建C	D030横断歩道橋基本	1	地建C
	諸元			datJ000	地建	D030横断歩道橋基本	9	地建

各データを統合し、共通項目を一元化するときは、左側のシステム記載内容を優先

※ 選択式の項目で、選択肢が各データで異なる場合、選択する内容（記載）が一致しないことはありますが、各データで選択する内容に齟齬がないか確認をお願いします。

＜選択式の項目例＞

77条調査データ	
コード	内容
1	単柱式
2	複柱式
3	逆L型
4	F型
5	テーパーポール型
6	T型
7	Y型
8	直線
9	門型
10	添架
80	その他

点検記録様式	
コード	内容
1	路側式
2	片持式（逆L型）
3	片持式（F型）
4	片持式（テーパーポール型）
5	片持式（T型）
6	門形式（オーバーヘッド型）
7	添架式
8	その他
9	ポール照明方式（テーパーポール型）
10	ポール照明方式（直線型）
11	ポール照明方式（Y型）
12	添架式
13	トンネル照明
14	その他

道路施設基本データ	
コード	区 分
11	単柱式
21	複柱式
31	逆L型
41	F型
42	テーパーポール型
43	T型
44	オーバーヘッド型

3.3. 道路施設基本データの登録

① 点検する施設が初回点検で新設の道路施設基本データがある場合や、補修工事後で道路施設基本データがある場合は、発注者からデータを受け取り、附属物ＤＢに登録してください。

② 登録するデータは、「3.2 クレンジング」を行い、共通項目について、77 条調査データや点検記録様式と記載内容を統一して登録してください。

※ 登録方法については、道路附属物 DB や http://www.rirs.or.jp/tenken-db/touroku.php に掲載されている操作マニュアルを参照。

※ 設計変更の対象となります。

※ 道路管理データ更新登録業務での登録も可能としますが、その場合は、過去の点検調書と登録内容に不整合が無いか確認を行ったうえで登録を行ってください。

※ 道路施設基本データに必要な項目が記載されていない場合のデータ補完や、完成図面等との照合によるデータ修正等を行って登録をお願いします。

4.　横断歩道橋

横断歩道橋で実施する作業の概要は、以下の通りです。

	名寄せ	クレンジング	維持的作業一覧表の登録	道路施設基本データの登録
準備段階		・点検した施設の道路施設基本データを、附属物ＤＢから探して取得		
点検結果ＤＢ登録時		・共通項目について、道路施基本データ・点検記録様式・７７条調査データで、記載の違いがあるか確認 ・違いがあるときは、記載内容を発注者に確認し、統一した記載をＤＢに登録		

4.1. クレンジング

① 点検する施設の道路施設基本データを、附属物ＤＢから取得します。

参考：道路施設基本データの取得方法

✓ 附属物ＤＢにログイン後、左側ツールバーの「道路施設基本データ」及び「一覧表示」を、順にクリック。

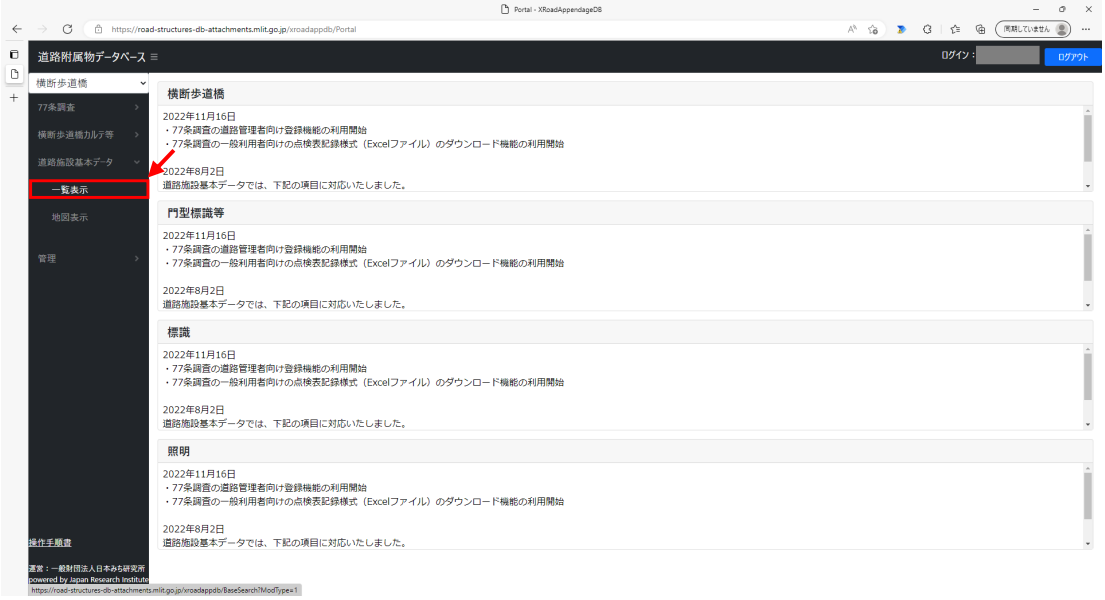

✓ 目的の施設を検索後、「台帳」マークをクリックし道路台帳の Excel ファイルを取得。

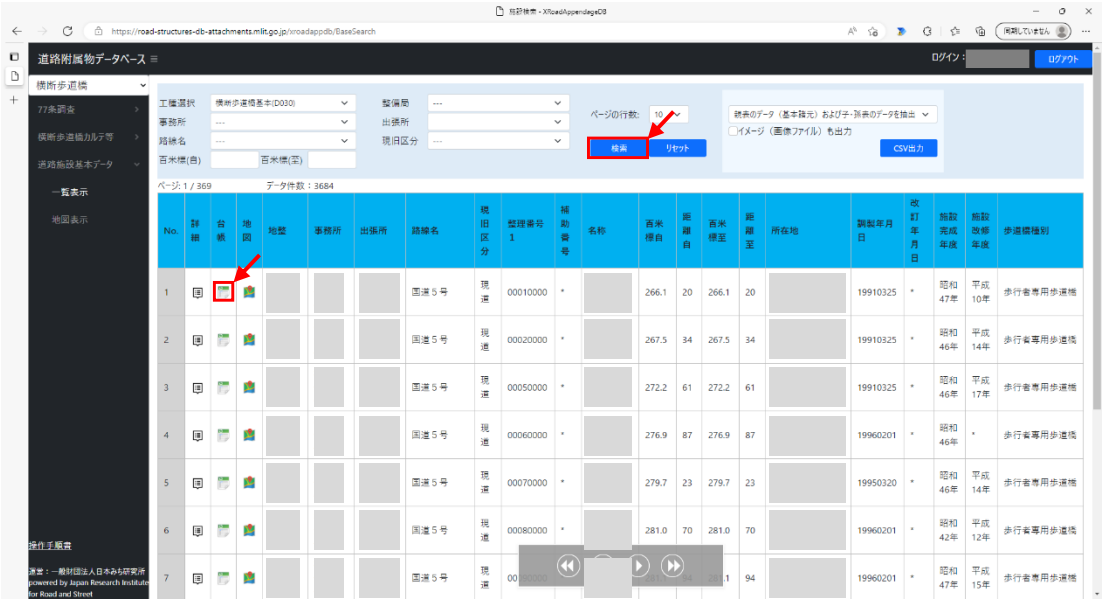

② 以下の「横断歩道橋 共通項目一覧表」に示す共通項目について、①で取得した道路施設基本データと、今回登録する 77 条調査データ、点検記録様式で、記載の違いがあるか確認します。

＜横断歩道橋 共通項目一覧表＞

77 条調査データ		横断歩道橋カルテ等	道路施設基本データ
施設名	横断歩道橋名	名称	名称
	ﾌﾘｶﾞﾅ	名称フリガナ	
路線	路線名	路線名称	路線
架設年度	架設年度（西暦）	架設竣工年	施設完成年度
橋長（m）		橋長	橋長
通路幅員（m）		有効幅員	幅員
形式区分			昇降形式 C
			昇降形式
管理者	管理者名	地建C	地建 C
		地建	地建
	管理事務所名	事務所C	事務所 C
		事務所	事務所
		出張所C	出張所 C
		出張所	出張所
行政区域	都道府県名	起点側所在地	所在地
	市区町村名	起点側所在地	
起点側の位置	緯度	北緯	緯度自
	経度	東経	経度自
	距離標（キロポスト）	百米標自	百米標自
		距離自	距離自
		現旧区分C	現旧区分 C
		現旧区分	現旧区分
		百米標至	百米標至
		距離至	距離至
		構造形式C	上部工構造形式 C
		構造形式	上部工構造形式
		材料区分C	上部工材料 C
		材料区分	上部工材料
		床版材料C	床版材料 C
		床版材料	床版材料
		橋台橋脚構造形式C	下部工形式 C
		橋台橋脚構造形式	下部工形式
		基礎形式C	基礎形式 C
		基礎形式	基礎形式
		総径間数	径間数
		橋面積	橋面積
		適用示方書C	適用示方書 C
		適用示方書	適用示方書
		設計震度	設計震度
		排水施設C	排水形式 C

77 条調査データ		横断歩道橋カルテ等	道路施設基本データ
		排水施設	排水形式
		左側車線地覆幅	地覆幅
		右側車線地覆幅	
		左側車線地覆高	地覆高さ
		右側車線地覆高	
		高欄防護柵別C	高欄材質構造形式 C
		高欄防護柵別	高欄材質構造形式
		東経至	経度至
		北緯至	緯度至
		プライマー下塗塗料1C	下塗塗料 C
		プライマー下塗塗料2C	
		プライマー下塗塗料1	下塗塗料
		プライマー下塗塗料2	
		プライマー下塗塗料1その他	
		プライマー下塗塗料2その他	
		中塗塗料1C	中塗塗料 C
		中塗塗料2C	
		中塗塗料1	中塗塗料
		中塗塗料2	
		中塗塗料1その他	
		中塗塗料2その他	
		上塗塗料1C	上塗塗料 C
		上塗塗料2C	
		上塗塗料1	上塗塗料
		上塗塗料2	
		上塗塗料1その他	
		上塗塗料2その他	
		年月日	補修年月
		内容	補修内容

③ 記載が異なる場合は、発注者に記載内容を確認し、登録するデータや附属物ＤＢのデータについて、記載内容を統一して登録します。過去の点検結果を書き換えるのではなく、新たに登録する点検結果や施設諸元について記載を統一してください。

【クレンジングの例】

７７条調査データ		横断歩道橋カルテ等		道路施設基本データ	
橋長（m）	５１．４	橋長	５１．６	橋長	５１．６
距離標（キロポスト）	９２．６７０	百米標自	９２．５	百米標自	９２．５
		距離自	７０	距離自	７０

７７条調査データ		横断歩道橋カルテ等		道路施設基本データ	
橋長（m）	５１．６	橋長	５１．６	橋長	５１．６
距離標（キロポスト）	９２．６７０	百米標自	９２．６	百米標自	９２．６
		距離自	７０	距離自	７０

※ 各データの登録方法については、道路附属物 DB や http://www.rirs.or.jp/tenken-db/touroku.php に掲載されている操作マニュアルを参照してください。

※ 今後、各データを統合し、共通項目を一元化する予定であり、その際には、

77 条調査データ　→　点検記録様式・カルテ　→　道路施設基本データ

の順に優先して記載内容を残す予定です。

（例．点検記録様式と道路施設基本データの共通項目で記載が異なっている場合、点検記録様式の記載を残し、道路施設基本データの記載を削除）

※ そのため、記載の優先順位の高いデータの記載を修正すれば、必ずしも全てのデータを修正する必要はありません。

	77条調査データ			横断歩道橋カルテ等		道路施設基本データ等		
8	諸元	施設名	横断歩道橋名	datK000_1	名称	D030横断歩道橋基本	14	名称
9	諸元		ﾌﾘｶﾞﾅ	datK000_1	名称フリガナ			
10	諸元	路線	路線名	datK000_1	路線名称	D030横断歩道橋基本	4	路線
12	諸元	架設年度	架設年度(西暦)	datK000_1	架設竣工年	D030横断歩道橋基本	22	施設完成年度
15	諸元	橋長(m)		datK000_2	橋長	D030横断歩道橋基本	51	橋長
16	諸元	通路幅員(m)		datK001	有効幅員	D030横断歩道橋基本	55	幅員
17	諸元	形式区分				D030横断歩道橋基本	36	昇降形式C
	諸元					D030横断歩道橋基本	37	昇降形式
19	諸元	管理者	管理者名	datJ000	地建C	D030横断歩道橋基本	1	地建C
	諸元			datJ000	地建	D030横断歩道橋基本	9	地建

各データを統合し、共通項目を一元化するときは、左側のシステム記載内容を優先

※ 選択式の項目で、選択肢が各データで異なる場合、選択する内容（記載）が一致しないことはありますが、各データで選択する内容に齟齬がないか確認をお願いします。

＜選択式の項目例＞

77条調査データ	
コード	内容
1	階段式
2	スロープ式
3	押上げ式
4	階段・スロープ併用式

道路施設基本データ	
コード	区 分
1	階 段 式
2	押 上 式
3	スロープ式
9	そ の 他